Test Ch01 — Description

Map test — tmap static

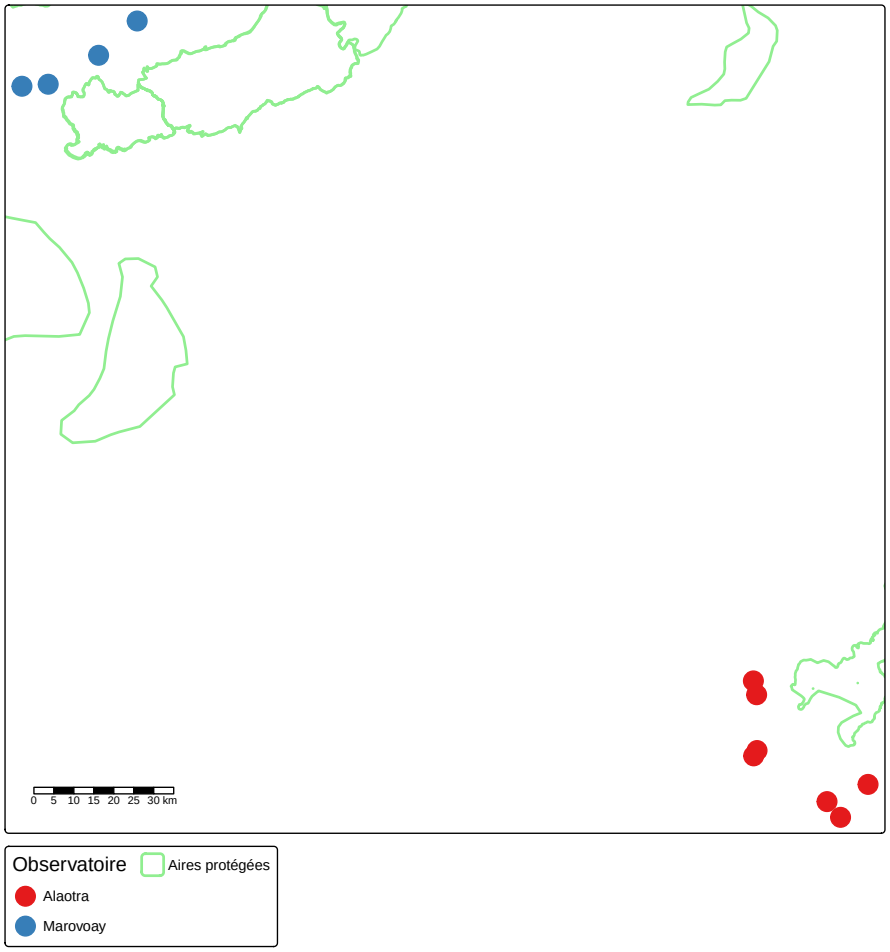

Figure 1 – Localisation approximative des fokontany enquêtés

Tables from Ch01

Table : Répartition des ménages

Table : Dénombrement

Table : Ménages par hameau (grouped)

Figure : Chronogramme

Figure : Enquêteurs

Table : Superviseurs (wide)

Table 1 – Répartition des ménages et des individus selon les observatoires

Observatoire	M			
'enages	Individus	% m		
'enages	% individus			
Marovoay	519	2 297	50.6	53.8
Alaotra	507	1 975	49.4	46.2
Ensemble	**1 026**	**4 272**	**100.0**	**100.0**

Source : Enquête auprès des OR 2025

Table 2 – Dénombrement et taux de sondage par observatoire

Observatoire	Toits d'enombrements	Ménages d'enombrés	Ménages enquêtés	Taux de sondage (%)
Alaotra	6 142	6 210	507	8.2
Marovoay	2 370	2 506	519	20.7

Source : Synthèse Dénombrement OR 2025 & Enquête auprès des OR 2025

Table 3 – Répartition des ménages enquêtés par hameau

Hameau	Ménages	% obs.
Alaotra		
Avaradrano	90	17.8
Feramanga Atsimo	89	17.6
Mangabe	73	14.4
Ambatomanga	68	13.4
Ambodivoara	58	11.4
Ambohidrony	52	10.3
Analamiranga	46	9.1
Ambatoharanana	31	6.1
Ensemble	**507**	**100.0**
Marovoay		
Ampijoroa	143	27.6
Madiromiongana	137	26.4
Bepako	123	23.7
Maroala	116	22.4
Ensemble	**519**	**100.0**

Source : Enquête auprès des OR 2025

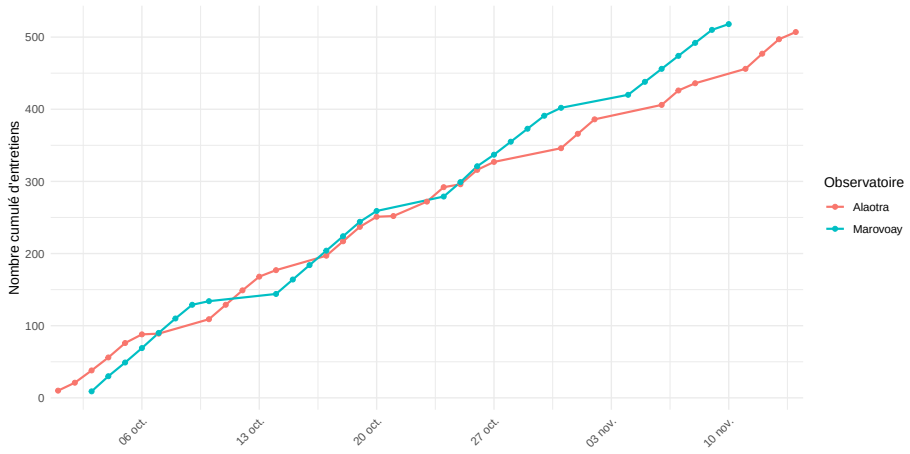

FIGURE 2 – Fréquences cumulées des entretiens par observatoire

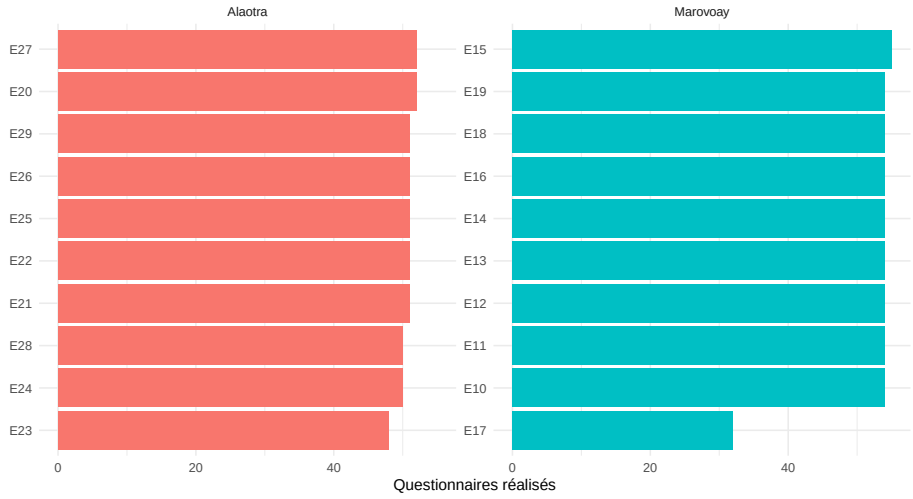

FIGURE 3 – Nombre de questionnaires par enquêteur et observatoire

TABLE 4 – Nombre de questionnaires supervisés par superviseur

Superviseur	Alaotra	Marovoay
S01	172	86
S02	166	217
S03	169	216

Source : Enquête auprès des OR 2025